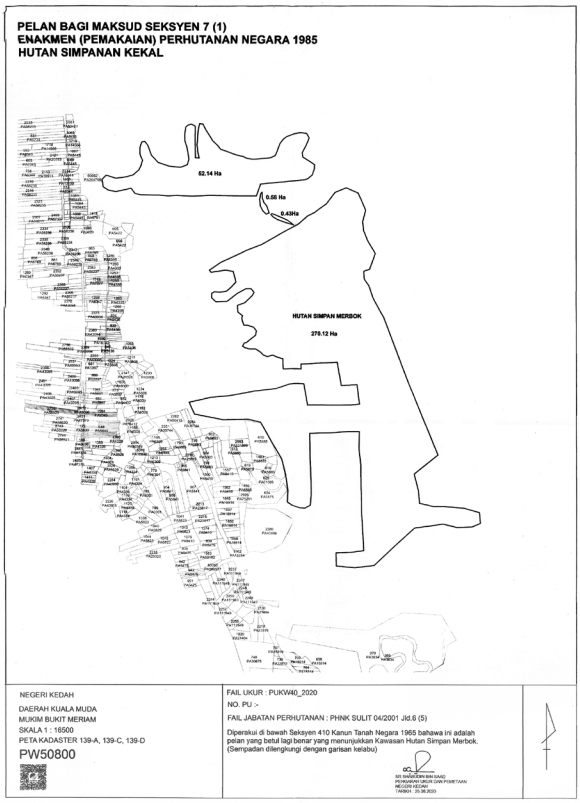

Bertarikh 10 Oktober 2021

Dated 10 October 2021

[PSU(K) 611-1440 Jld. 4/PHNK SULIT 4/2001 Jld. 6(5)]

MOHAMAD AZLEE BIN AHMAD
Setiausaha Majlis Mesyuarat Kerajaan Kedah/
Secretary Kedah State Executive Council Kedah

No. 453.

PEMBERITAHUAN DI BAWAH SEKSYEN 7

NOTIFICATION UNDER SECTION 7

Pada menjalankan kuasa yang diberikan oleh seksyen 7 Enakmen (Pemakaian) Perhutanan Negara 1985, Pihak Berkuasa Negeri mengisytiharkan tanah seluas 1134.53 hektar yang ditandakan di atas Pelan Ukur No. P.W. 50805 yang disimpan di Pejabat Pengarah Ukur dan Pemetaan Kedah menjadi hutan simpan kekal dikenali sebagai Hutan Simpan Terenas Tambahan, Mukim Jeneri, Daerah Sik, Kedah mulai tarikh pemberitahuan ini disiarkan dalam *Warta*.

In exercise of the powers conferred by section 7 of National Forestry (Adoption) Enactment 1985, State Authority declares the land comprising an area of 1134.53 hectares as delineated upon Survey Plan No. P.W. 50805 deposited in the Office of Director of Survey and Mapping of Kedah to be permanent reserved forest to be known as Terenas Tambahan Reserved Forest, Mukim Jeneri, District Sik, Kedah from the date of publication of this notification in the *Gazette*.

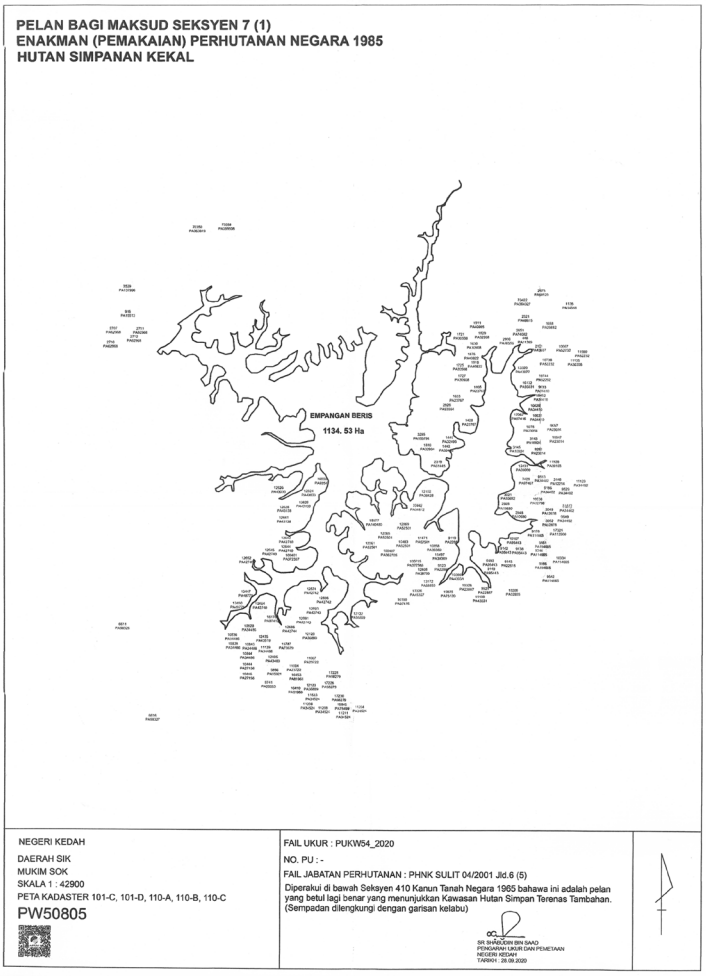

Bertarikh 10 Oktober 2021

Dated 10 October 2021

[PSU(K) 611-1440 Jld. 4/PHNK SULIT 4/2001 Jld. 6(5)]

MOHAMAD AZLEE BIN AHMAD
Setiausaha Majlis Mesyuarat Kerajaan Kedah/
Secretary Kedah State Executive Council Kedah

No. 454.

PEMBERITAHUAN DI BAWAH SEKSYEN 7

NOTIFICATION UNDER SECTION 7

Pada menjalankan kuasa yang diberikan oleh seksyen 7 Enakmen (Pemakaian) Perhutanan Negara 1985, Pihak Berkuasa Negeri mengisytiharkan tanah seluas 590.5 hektar yang ditandakan di atas Pelan Ukur No. P.W. 50801 yang disimpan di Pejabat Pengarah Ukur dan Pemetaan Kedah menjadi hutan simpan kekal dikenali sebagai Hutan Simpan Rimba Teloi, Mukim Sok, Daerah Sik, Kedah mulai tarikh pemberitahuan ini disiarkan dalam *Warta*.

In exercise of the powers conferred by section 7 of National Forestry (Adoption) Enactment 1985, State Authority declares the land comprising an area of 590.5 hectares as delineated upon Survey Plan No. P.W. 50801 deposited in the Office of Director of Survey and Mapping of Kedah to be permanent reserved forest to be known as Rimba Teloi Reserved Forest, Mukim Sok, District Sik, Kedah from the date of publication of this notification in the *Gazette*.

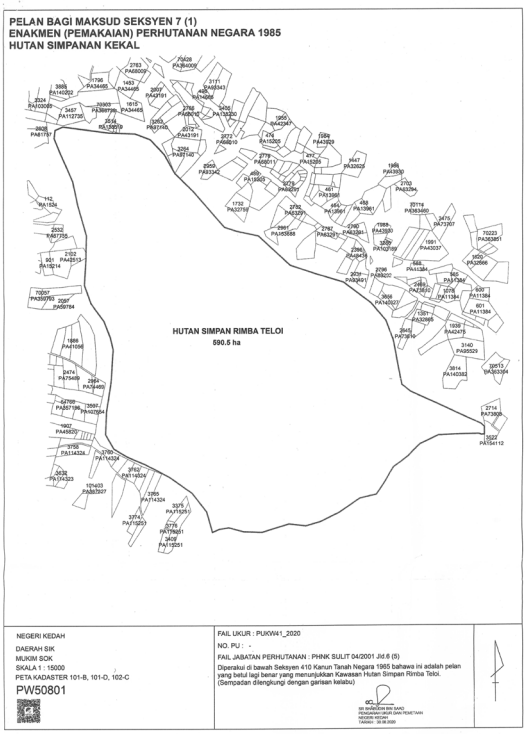

Bertarikh 10 Oktober 2021

Dated 10 October 2021

[PSU(K) 611-1440 Jld. 4/PHNK SULIT 4/2001 Jld. 6(5)]

MOHAMAD AZLEE BIN AHMAD
Setiausaha Majlis Mesyuarat Kerajaan Kedah/
Secretary Kedah State Executive Council Kedah