LAPORAN KAJIAN SEMAKAN SEPARUH PENGGAL RANCANGAN PENGURUSAN HUTAN NEGERI SELANGOR

2021-2030

Jabatan di jaga. Adalah wajar perancangan di buat untuk memastikan jumlah kakitangan dikekal terus sehingga 2030.

Jadual 3.5g Sumber modal insan Jabatan Perhutanan Negeri Selangor

Perjawatan	2021	2022	2023	2024
Professional	14	14	14	14
Sokongan	371	367	367	368
Jumlah	**385**	**381**	**381**	382

3.5.7 Kutipan Hasil

Melalui semakan dokumen RPH Selangor 2021–2030, didapati bahawa jumlah kutipan hasil semenjak tahun 2021 hingga tahun 2024 adalah sebanyak RM 195,147,664.08 juta. Kutipan ini adalah daripada royalti kayu balak, royalti keluaran hasil hutan kecil, premium, denda dan gantirugi serta fi pelesenan, pentadbiran dan sebagainya.

Jumlah kutipan hasil hutan setiap tahun dalam tempoh 2021-2024 adalah seperti di **Jadual 3.5h**. Terdapat peningkatan dalam kutipan hasil pelbagai dari RM43.95 juta pada tahun 2021 ke RM44.00 juta pada tahun 2024 kerana kadar premium telah dinaikkan dari RM600/ha kepada RM3,000/ha untuk Hutan Dara, RM2,500/ha untuk Hutan Terpulih dan RM2,000/ha untuk Hutan Dibalak mulai tahun 2007. Kutipan ses menurun daripada RM3.02 juta pada tahun 2021 kepada RM2.93 juta pada tahun 2024.

Jadual 3.5h. Kutipan hasil Jabatan bagi tempoh 2021-2024 (RM)

Tahun	Cukai/Royalti	Lesen Hutan	Gantirugi	Kompaun & Kenaan Hutan	Premium & Cukai Hutan	Pelbagai	Ses	Lain-lain Sumber	Hasil Tahun Lalu	Kutipan Daerah	Jumlah Hasil
2021	35,794,736.35	1,301,538.10	878,718.76	118,100.00	1,467,869.84	63,865.00	3,015,114.95	0.00	838,818.15	468,985.35	43,947,746.50
2022	38,018,100.56	1,826,667.50	1,535,654.94	129,160.80	0.00	111,888.70	3,168,175.16	0.00	240,370.00	1,060,635.00	46,090,652.66
2023	34,988,078.49	1,574,363.50	17,935,846.69	337,285.00	0.00	99,738.50	2,920,845.79	0.00	2,122,829.22	1,128,629.05	61,107,616.24
2024	35,040,584.12	2,077,870.50	1,234,787.31	277,300.00	0.00	107,495.00	2,932,926.56	0.00	795,654.86	1,535,030.33	44,001,648.68
JUMLAH	**143,841,499.52**	**6,780,439.60**	**21,585,007.70**	**861,845.80**	**1,467,869.84**	**382,987.20**	**12,037,062.46**	**0.00**	**3,997,672.23**	**4,193,279.73**	**195,147,664.08**

*Sumber : *Data diperolehi dari Pejabat Perhutanan Negeri Selangor*
***Laporan Tahunan Jabatan Perhutanan Negeri Selangor, 2021-2024*

3.6 Maklumat Asas Sumber Hutan

3.6.1 Keluasan dan Jenis Hutan

Negeri Selangor dengan keluasan berjumlah 792,116.09 ha (PLANMalaysia, 2021) merupakan sebuah negeri yang maju dan moden, dan pada masa yang sama masih dapat mengekalkan banyak kawasan di negeri ini sebagai kawasan perlindungan dan berhutan.

Terdapat tiga (3) jenis hutan yang utama di Negeri Selangor iaitu Hutan Darat, Hutan Paya Laut dan Hutan Paya Gambut seperti **Rajah 3.6a**. Manakala **Jadual 3.6a** pula menunjukkan pecahan kawasan berhutan termasuk cadangan HSK (CHSK), ladang hutan, taman hidupan liar dan tanah kerajaan. Secara asasnya, kawasan ladang hutan di Negeri Selangor berada di dalam kawasan HSK. Maklumat terperinci HSK yang telah diwartakan termasuk keluasan HSK di Negeri Selangor bagi Hutan Darat, Hutan Paya Laut dan Hutan Paya Gambut adalah seperti di **Jadual 3.6b**, **Jadual 3.6c** dan **Jadual 3.6d**. Pentadbiran hutan Negeri Selangor dipecahkan kepada tiga (3) Daerah Pentadbiran Hutan yang utama yang telah ditentukan sempadannya. Pentadbiran Hutan Daerah yang dimaksudkan adalah Selangor Tengah, Hulu Selangor dan Pantai Klang.

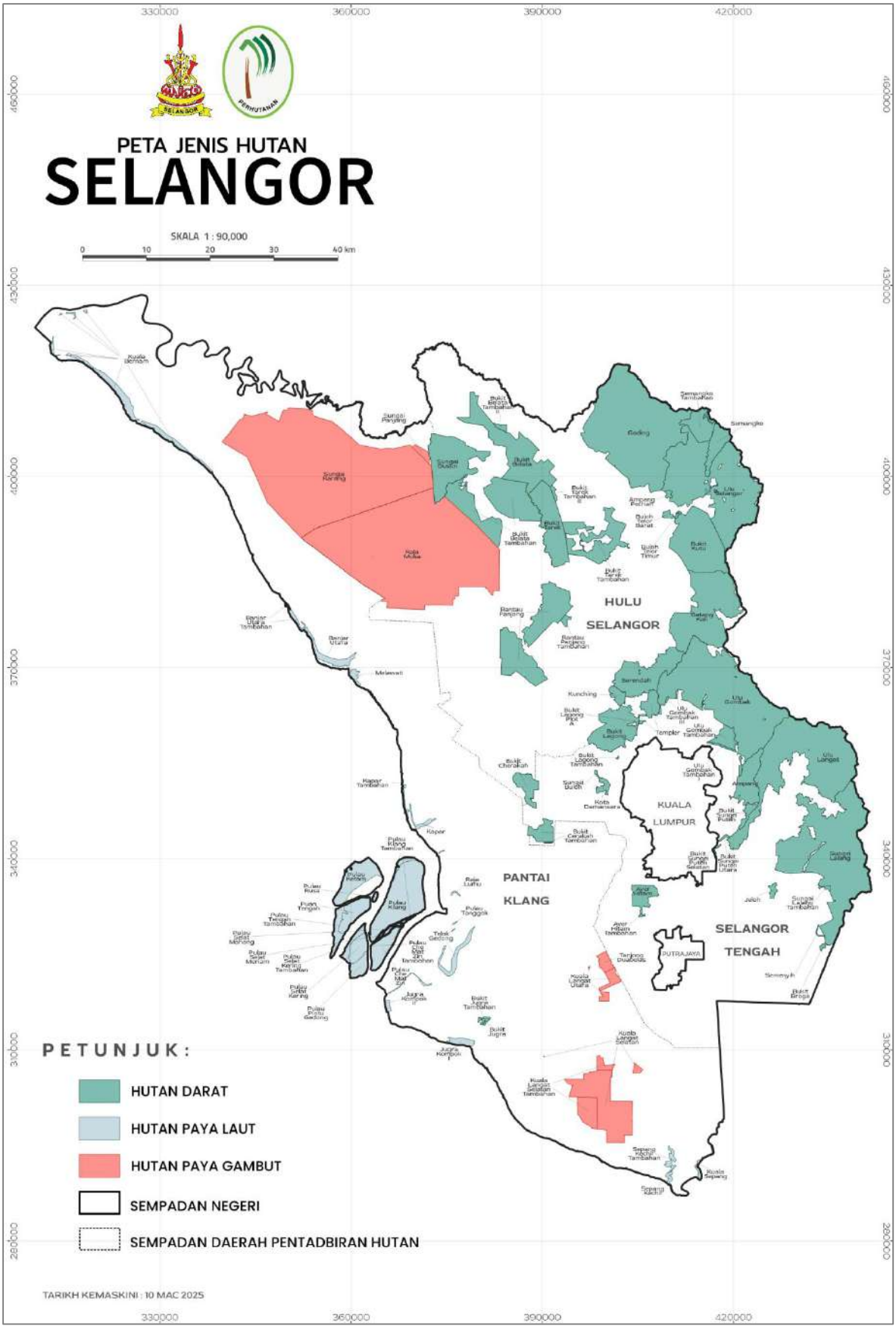

Rajah 3.6a Peta taburan jenis hutan yang terdapat di Negeri Selangor

Jadual 3.6a Maklumat sumber hutan Negeri Selangor sehingga Disember 2024

Sumber Hutan	Keluasan (ha)
HSK (Termasuk Ladang Hutan)	250,987.12
i. Hutan Darat	148,593.34
ii. Hutan Paya Gambut	83,147.99
iii. Hutan Paya Laut	19,245.79
CHSK	299.11
i. Hutan Darat	299.11
ii. Hutan Paya Gambut	-
iii. Hutan Paya Laut	-
Tanah Kerajaan	649.37
Hutan Taman Hidupan Liar	
i. Rezab Hidupan Liar (Dalam HSK)	6,850.87
ii. Rezab Hidupan Liar (Luar HSK)	225.00

Jadual 3.6b Senarai HSK untuk Hutan Darat di Negeri Selangor sehingga Disember 2024

Bil.	Daerah Hutan	Nama HSK	Tarikh Warta	No. Warta/ Pelan Warta	Keluasan Hutan Darat (ha)
1	Selangor Tengah	Sungei Buloh	14/01/1898	9	25.00
2	Selangor Tengah	Ulu Gombak	11/5/1906	297	16,847.46
3	Hulu Selangor	Bukit Kutu	14/9/1906	589	6,515.99
4	Selangor Tengah	Ayer Itam	23/11/1906	743	1,159.81
5	Selangor Tengah	Sungei Lalang	22/11/1907	846	17,027.77
6	Hulu Selangor	Bukit Cherakah	21/5/1909	278	1,298.86
7	Hulu Selangor	Rantau Panjang	25/11/1910	2408	6,815.62
8	Hulu Selangor	Bukit Belata	23/12/1911	2993	6,101.16
9	Selangor Tengah	Bukit Sungei Puteh	20/6/1913	1692	440.78
10	Selangor Tengah	Ampang	19/12/1913	3703	2,307.87
11	Selangor Tengah	Bukit Sungai Puteh (Tambahan)	2/1/1914	45	34.77
12	Hulu Selangor	Bukit Tarek	25/9/1914	2885	3,323.83
13	Hulu Selangor	Semangko	11/2/1916	486	1,540.79
14	Hulu Selangor	Gading	15/2/1917	322	18,934.32
15	Hulu Selangor	Bukit Lagong	21/12/1917	3695	3,595.80
16	Hulu Selangor	Batang Kali	25/2/1921	784	8,475.91
17	Selangor Tengah	Ulu Langat	21/1/1927	388	13,463.92
18	Selangor Tengah	Jeloh	19/8/1927	4416	203.62
19	Hulu Selangor	Ampang Pechah	8/5/1931	3313	126.41
20	Hulu Selangor	Kanching	8/5/1931	1431	447.38
21	Hulu Selangor	Serendah	13/5/1931	3314	4,082.50
22	Pantai Klang	Bukit Jugra	12/5/1959	243	68.70
23	Pantai Klang	Bukit Jugra (Tambahan)	13/9/1962	879	72.00
24	Hulu Selangor	Bukit Belata Tambahan	13/1/1966	14	6,747.31
25	Hulu Selangor	Bukit Tarek Tambahan	28/7/1966	353	3,387.22
26	Hulu Selangor	Ulu Selangor	31/7/1969	423	15,025.14
27	Hulu Selangor	Templer	27/4/1995	537	813.71
28	Hulu Selangor	Rantau Panjang (Tambahan)	12/9/1996	759	150.71
29	Selangor Tengah	Bukit Cerakah (Tambahan)	27/9/2007	2614	967.73
30	Hulu Selangor	Semangko (Tambahan)	12/2/2009	493	1,611.00
31	Hulu Selangor	Bukit Belata (Tambahan II)	4/6/2009	1797	146.00
32	Hulu Selangor	Bukit Tarek (Tambahan II)	4/6/2009	1796	112.00
33	Selangor Tengah	Sungei Lalang (Tambahan)	4/6/2009	1798	72.00
34	Hulu Selangor	Sungai Dusun	18/2/2010	399	4,891.39
35	Selangor Tengah	Kota Damansara	18/2/2010	398	321.75

Bil.	Daerah Hutan	Nama HSK	Tarikh Warta	No. Warta/ Pelan Warta	Keluasan Hutan Darat (ha)
36	Selangor Tengah	Ulu Gombak (Tambahan I)	18/2/2010	401	114.48
37	Selangor Tengah	Ulu Gombak (Tambahan)	18/2/2010	400	897.59
38	Selangor Tengah	Ayer Hitam (Tambahan)	22/7/2010	2460	22.26
39	Hulu Selangor	Bukit Lagong Tambahan	22/6/2017	2192/ PW 1892	40.46
40	Selangor Tengah	Ulu Gombak (Tambahan III)	22/6/2017	2193/ PW 1894	60.07
41	Selangor Tengah	Bukit Broga	12/8/2021	1814/3016	63.88
42	Hulu Selangor	Buloh Telor Barat	12/8/2021	1812/3020	149.96
43	Hulu Selangor	Buloh Telor Timur	12/8/2021	1813/3020	57.18
44	Selangor Tengah	Semenyih	24/8/2023	2890/PW3047	31.23
Jumlah Keseluruhan Keluasan Kawasan HSK untuk Hutan Darat (ha)					**148,593.34**

Jadual 3.6c Senarai HSK untuk Hutan Paya Laut di Negeri Selangor sehingga Disember 2024

Bil.	Daerah Hutan	Nama HSK	Tarikh Warta	No. Warta/ Pelan Warta	Keluasan Hutan Paya Laut (ha)
1.	Pantai Klang	Pulau Che Mat Zin	11/11/1904	850	1,419.21
2	Pantai Klang	Pulau Klang	11/11/1904	850	5,611.81
3.	Pantai Klang	Pulau Pintu Gedong	11/11/1904	850	741.55
4.	Pantai Klang	Pulau Selat Kering	11/11/1904	850	932.77
5.	Pantai Klang	Pulau Selat Mahang	11/11/1904	850	148.88
6.	Pantai Klang	Pulau Selat Meriam	11/11/1904	850	53.81
7.	Pantai Klang	Jugra Kompok I	16/2/1912	468	418.98
8.	Pantai Klang	Jugra Kompok II	13/2/1914	450	85.88
9.	Pantai Klang	Telok Gedong	28/8/1914	2581	659.79
10.	Pantai Klang	Kapar	9/10/1914	2998	138.20
11.	Pantai Klang	Banjar Utara	15/1/1915	44	1,011.64
12.	Pantai Klang	Pulau Tengah	5/5/1916	1475	1,415.64
13.	Pantai Klang	Sepang Kechil	13/7/1923	4047	267.98
14.	Pantai Klang	Banjar Utara (Tambahan)	21/9/1923	5770	226.04
15.	Pantai Klang	Kapar (Tambahan)	30/5/1924	3543	44.18
16.	Pantai Klang	Sepang Kechil (Tambahan)	1/1/1929	5866	17.58
17.	Pantai Klang	Pulau Tonggok	7/10/1932	7421	33.65
18.	Pantai Klang	Kuala Sepang	24/10/1940	5656	160.51
19.	Pantai Klang	Kuala Bernam	19/12/1940	6718	846.50
20.	Pantai Klang	Telok Gedong (Tambahan)	17/2/1970	610	703.40
21.	Pantai Klang	Pulau Che Mat Zin (Tambahan)	6/5/2009	1794	43.00
22.	Pantai Klang	Pulau Ketam	6/5/2009	1790	2,365.00
23.	Pantai Klang	Pulau Klang (Tambahan)	6/5/2009	1793	268.00
24.	Pantai Klang	Pulau Rusa	6/5/2009	1791	85.00
25.	Pantai Klang	Pulau Selat Kering (Tambahan)	6/5/2009	1795	509.00
26.	Pantai Klang	Pulau Tengah (Tambahan)	6/5/2009	1792	790.00
27.	Pantai Klang	Raja Lumu	26/10/2023	3900/PW3053	38.75
28.	Pantai Klang	Melawati	4/1/2024	1/PW3055&PW3056	209.04
Jumlah Keseluruhan Keluasan Kawasan HSK untuk Hutan Paya Laut (ha)					**19,245.79**

Jadual 3.6d Senarai HSK untuk Hutan Paya Gambut di Negeri Selangor sehingga Disember 2024

Bil.	Daerah Hutan	Nama HSK	Tarikh Warta	No. Warta/ Pelan Warta	Keluasan Hutan Paya Gambut (ha)
1.	Pantai Klang	Kuala Langat Selatan	13/5/1927	2577	6,844.30
2.	Pantai Klang	Kuala Langat Utara	13/5/1927	2578	688.63
3.	Pantai Klang	Kuala Langat Selatan (Tambahan)	30/8/1934	3640	194.87
4.	Pantai Klang	Kuala Langat Selatan (Tambahan)	13/3/1940	1410-D	1,300.55
5.	Hulu Selangor	Raja Musa	8/1/1990	49	35,656.00
6.	Pantai Klang	Sungai Karang	8/1/1990	48	37,668.95
7.	Pantai Klang	Sungai Panjang	12/8/2021	1811/3021	308.62
8.	Pantai Klang	Tanjong Duabelas	27/7/2023	2395/PW3046	486.07
Jumlah Keseluruhan Keluasan Kawasan HSK untuk Hutan Paya Gambut (ha)					**83,147.99**

Maklumat keluasan HSK mengikut pentadbiran Pejabat Hutan Daerah adalah seperti **Jadual 3.6e** manakala **Rajah 3.6b** menunjukkan carta peratus keluasan HSK Mengikut Daerah Hutan sehingga Disember 2024.

Jadual 3.6e Keluasan HSK (ha) Mengikut Daerah Hutan sehingga Disember 2024

Daerah	Hutan Darat	Hutan Paya Gambut	Hutan Paya Laut	Jumlah
Selangor Tengah	54,061.99	-	-	54,061.99
Hulu Selangor	94,390.65	35,656.00	-	130,046.65
Pantai Klang	140.70	47,491.99	19,245.79	66,878.48
Jumlah	**148,593.34**	**83,147.99**	**19,245.79**	**250,987.12**

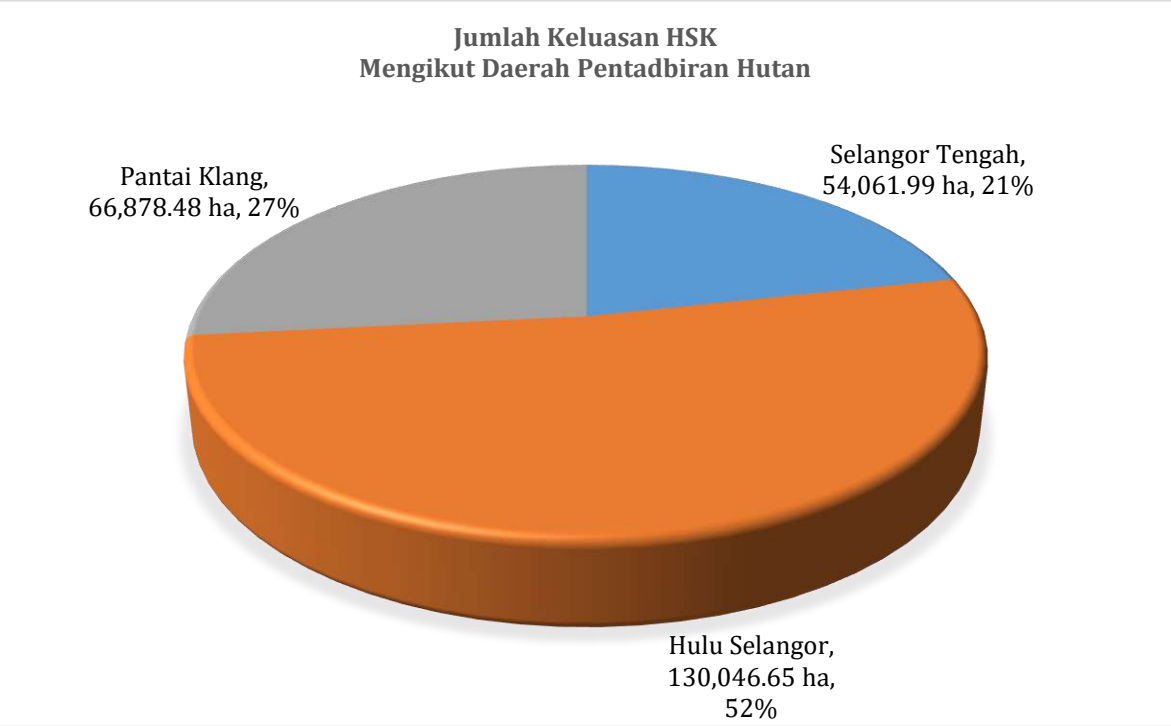

Rajah 3.6b Carta peratus dan keluasan HSK mengikut Daerah Hutan sehingga Disember 2024

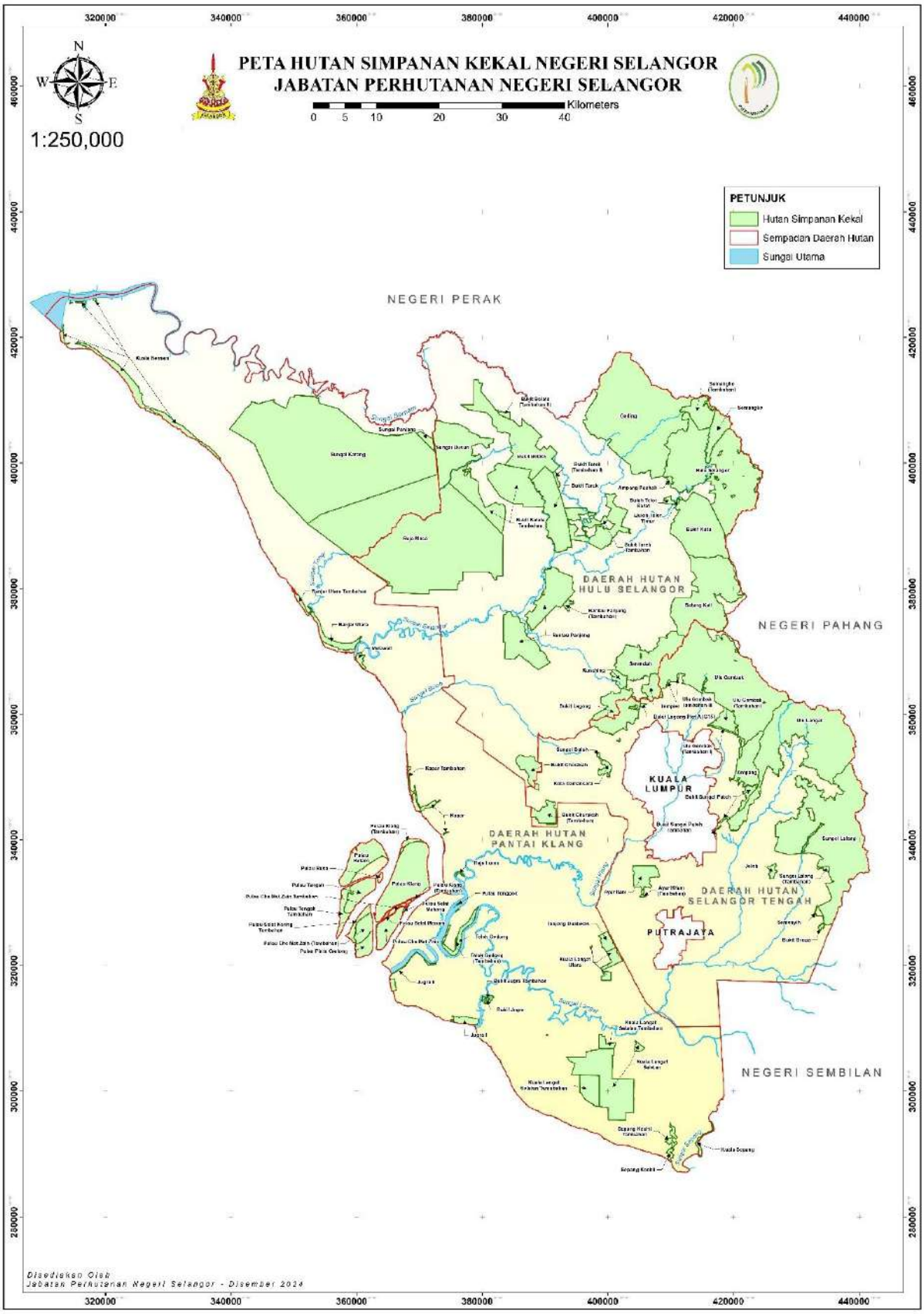

Rajah 3.6d Peta HSK Negeri Selangor

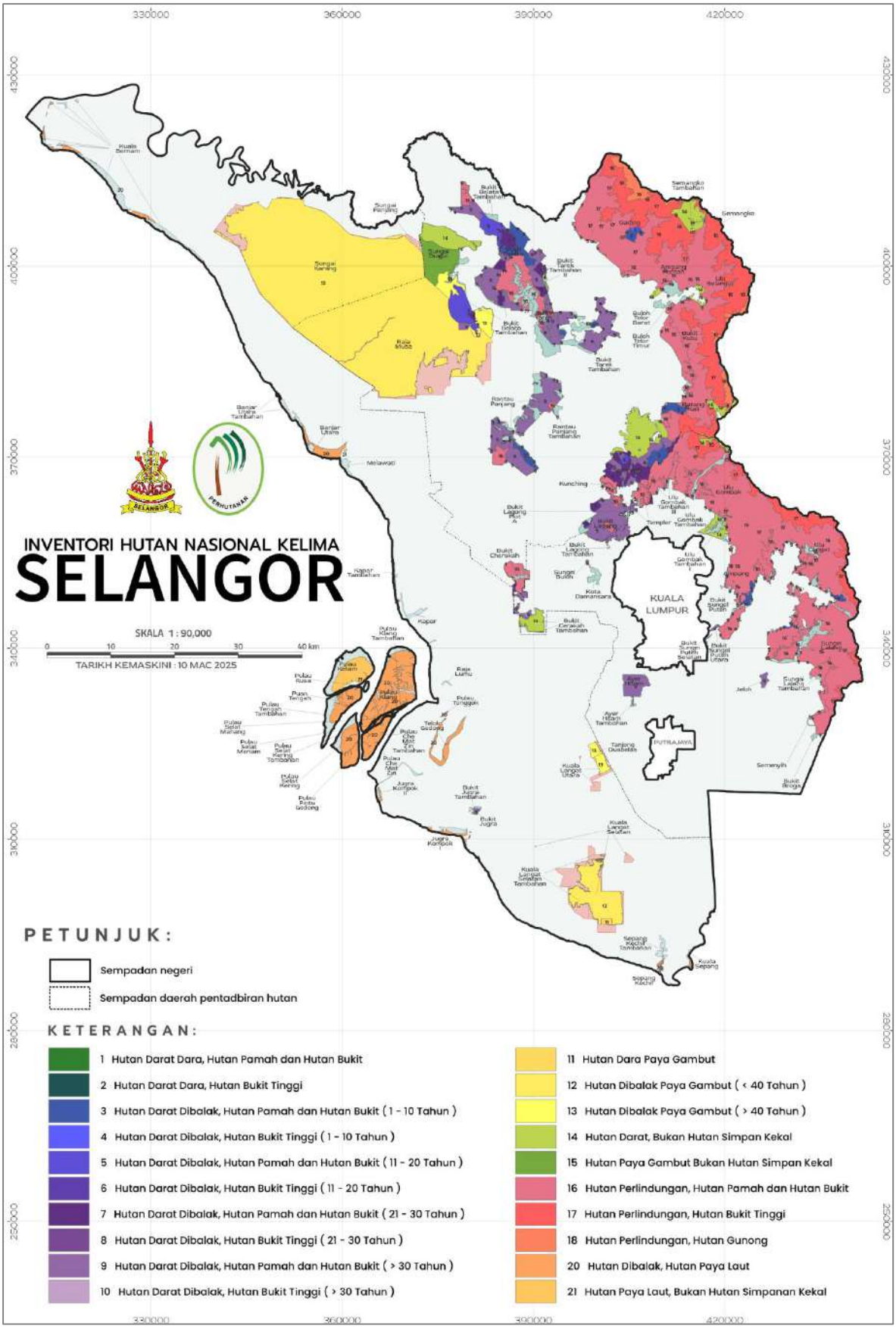

Rajah 3.6e Peta Inventori Hutan Nasional Kelima bagi Negeri Selangor