Draf RANCANGAN TEMPATAN DAERAH BATANG PADANG 2035 (PENGGANTIAN)

PLANMalaysia
Perancangan Melangakaui Kelaziman
Planning : Beyond Conventional
BAHAGIAN RANCANGAN PEMBANGUNAN
PEJABAT PROJEK ZON TENGAH

PLANMalaysia@Perak
Perancangan Melangakaui Kelaziman
Planning : Beyond Conventional

Majlis Daerah Tapah

JILID I
STRATEGI PEMBANGUNAN

B. Perhutanan

- Lima (5) fungsi hutan di Daerah Batang Padang. Antaranya adalah:

Hutan Tadahan Air

59, 845.38 ha

HSK Tahun 2018

69, 227.53 ha

Hutan Perlindungan Tanah >1000 meter

34, 352.25 ha

Central Forest Spine (CFS)

3,349.10 ha

Kawasan Pembalakan 2018 di Gunung Besout Kompartmen 19, 20, 21, 22 & 25

400.00 ha

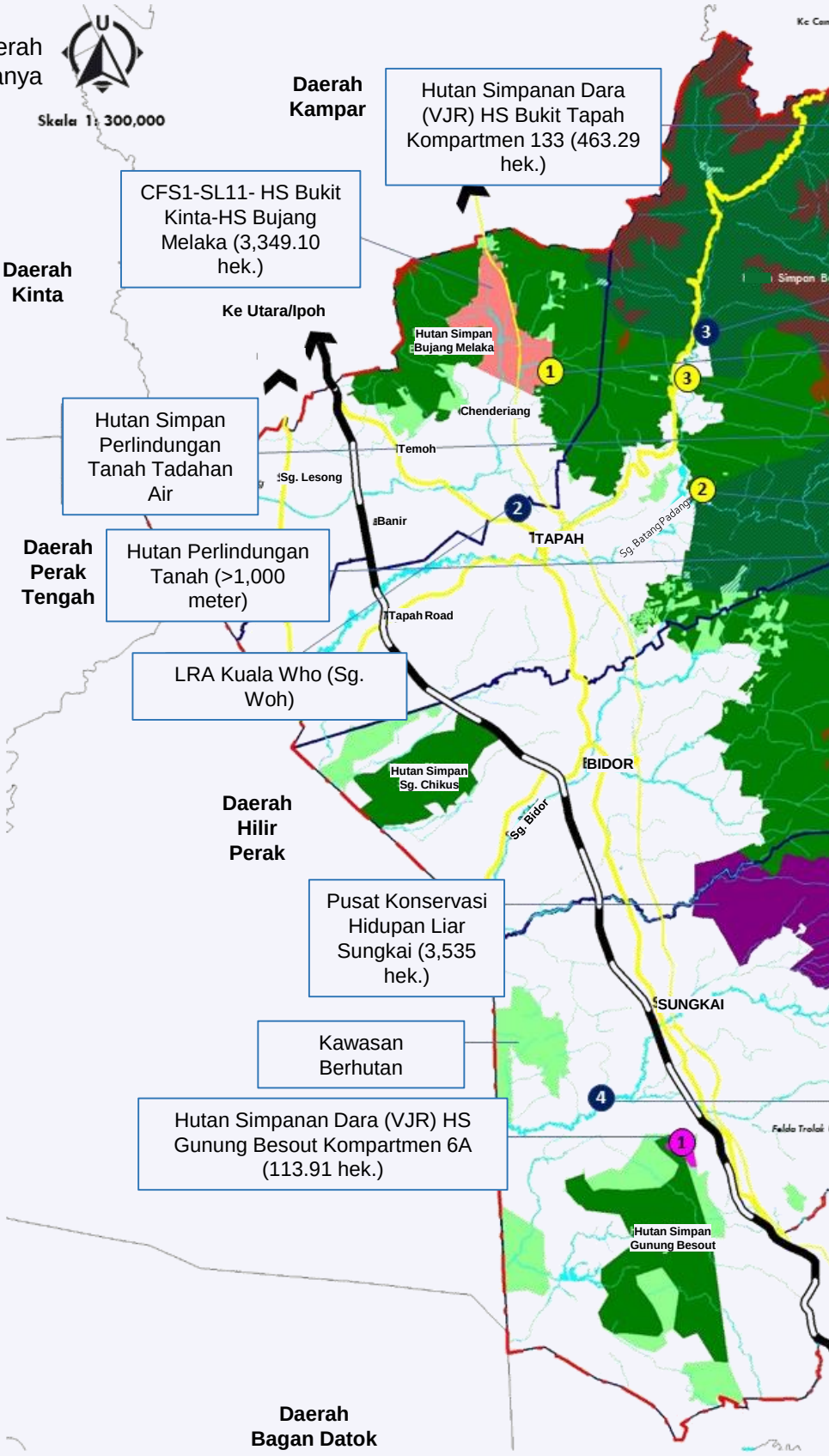

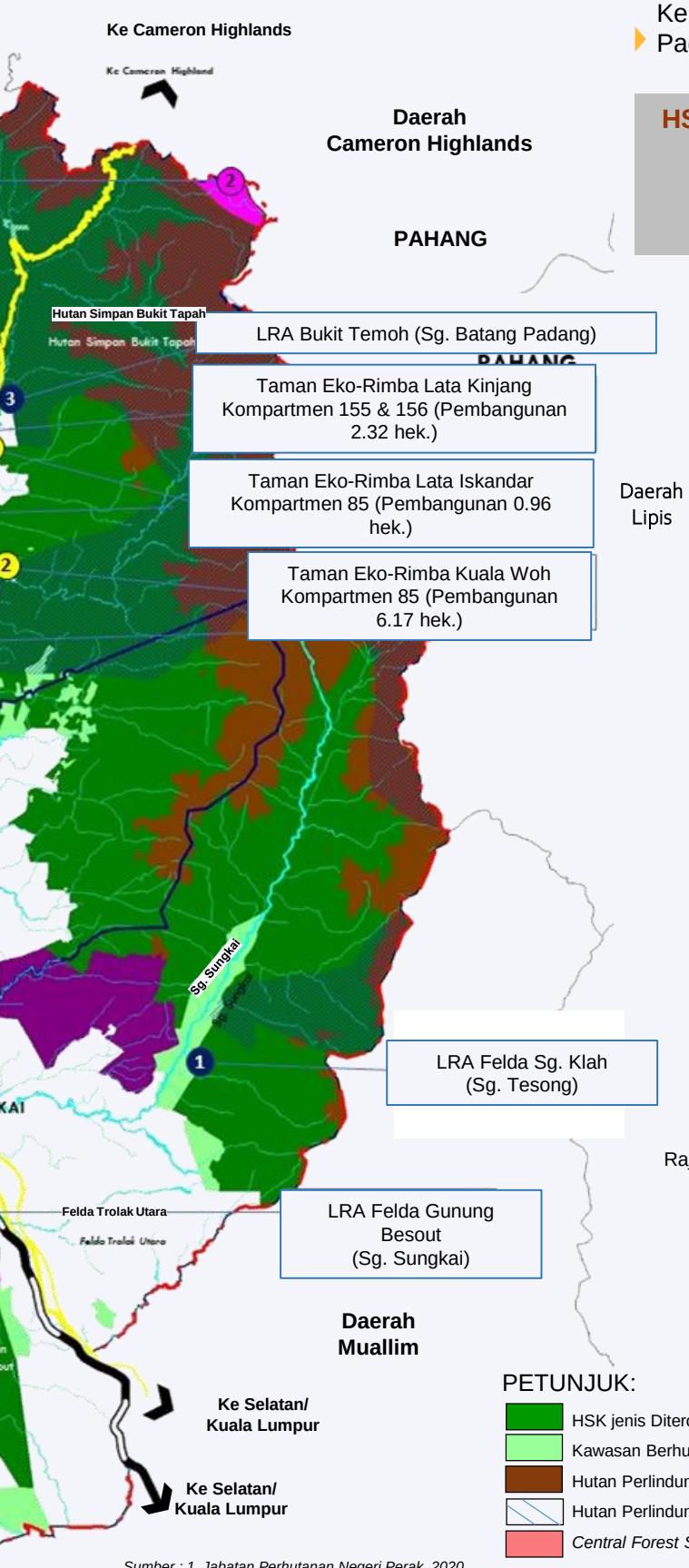

Keluasan hutan simpan kekal di Derah Batang Padang.

HSK Bujang Melaka 2018 (3, 103.51 ha) 4.5%

HSK Gunung Besout 2018 (2, 603.18 ha) 3.8%

HSK Bukit Tapah 2018 (61, 130.75 ha) 88.3%

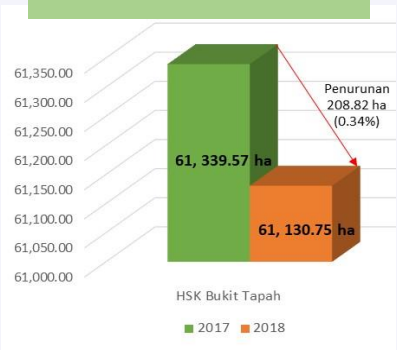

HSK Chikus 2018 (2, 390.09 ha) 3.4%

Rajah 3.23 : Keluasan hutan simpan kekal di Derah Batang Padang.

ISU:

ALM 2

Menterjemahkan dan memperincikan Pelan Induk CFS ke dalam kawasan kajian

PETUNJUK:

- HSK jenis Diterokarp Pamah
- Kawasan Berhutan
- Hutan Perlindungan Tanah (>1000 meter)
- Hutan Perlindungan Tanah Tadahan Air
- *Central Forest Spine (CFS)*

Sumber : 1. Jabatan Perhutanan Negeri Perak, 2020
2. Garis Panduan Perancangan KSAS, 2017
3. iPlan, PLANMalaysia, 2019
4. Kajian Rancangan Tempatan Daerah Batang Padang 2035 (Penggantian)